ETAPA PROPOSTA TÉCNICA | C1: VIAS SEGURAS

Município: Monte Mor

Código IBGE: 3531803

Protocolo de envio da proposta técnica: SRV1037004

Prezado(a),

Informamos que, após análise técnica realizada nos termos do Edital de Chamamento Público e considerando a avaliação do material submetido pelo município no âmbito do Programa Respeito à Vida (PRaVida), identificou-se a necessidade de **adequações e complementações no projeto e nas documentações apresentadas**, de modo a assegurar que a equipe técnica disponha dos subsídios necessários para a adequada avaliação da proposta, em conformidade com os critérios técnicos, normativos e programáticos estabelecidos para o **Componente 1: Vias Seguras**.

Nesse processo de análise, as propostas listadas abaixo foram classificadas entre: 1. aderentes aos requisitos técnicos do programa e, portanto, aptas para a revisão detalhada; 2. não aderentes aos requisitos técnicos e formais do componente e que, por isso, necessitariam de adequações estruturais, e; 3. sem a documentação necessária para análise técnica.

No anexo, encontram-se os pareceres técnicos detalhados, que integram esta devolutiva e apresentam as análises e os apontamentos específicos referentes aos projetos funcionais.

1. Propostas aderentes:

As propostas listadas a seguir foram objeto de análise técnica detalhada conforme os pareceres que integram o anexo deste documento. Através da avaliação, identificaram-se aspectos que necessitam de ajuste e complementação em relação às diretrizes de desenho viário seguro, bem como inconsistências técnicas que requerem revisão de acordo com as orientações do Edital e do Guia de Intervenções para Vias Seguras.

São elas:

- **AV. JÂNIO QUADROS**

2. Propostas não aderentes:

Não houve propostas não aderentes.

3. Propostas sem a documentação necessária para análise técnica:

Não houve propostas sem a documentação necessária para análise técnica.

Ressalvas e adequações gerais necessárias:

Documentação administrativa:

(x) Termo de Adesão: Documento não enviado.
( ) Ofício de Projeto Funcional
(x) Declaração de Capacitação em Visão Zero e Sistema Seguro: necessário anexar à declaração o certificado de capacitação referente a curso já realizado anteriormente, não sendo aceitos, para este fim, certificados de cursos previstos ou a serem realizados no ciclo atual do Programa Respeito à Vida.

Documentação Técnica:

(x) Apresentar o arquivo de georreferenciamento da intervenção (*.kmz*) conforme orientação técnica (páginas 12 e 13 do Manual Operacional do PRaVida).
( ) Outros:

Informações gerais:

‣As informações constantes nesses documentos devem estar compatíveis com o respectivo projeto apresentado e em conformidade com as diretrizes, requisitos e critérios estabelecidos no Edital e demais documentos orientadores do Programa Respeito à Vida (PRaVida);
‣Caso o Município apresente mais de uma proposta (ex.: Corredor Seguro 01, Área Calma 02 e/ou Cruzamento Compacto 03), deverá indicar a classificação de prioridade entre elas;
‣Arquivos com extensão *.kmz* e *.dwf* deverão ser compactados em pasta no formato *.zip* para que o sistema aceite sua inclusão no formulário.

Recomendações:

‣Recomenda-se a consulta da versão atualizada do **Manual Operacional do Programa Respeito à Vida** disponibilizada no portal do Detran-SP, especialmente no trecho referente à Proposta de Intervenção (páginas 15 a 22).

▸Recomenda-se a leitura atenta do **Guia de Intervenções para Vias Seguras**, documento orientador deste Componente, para a adequada caracterização da escala de intervenção, definição da abordagem de desenho viário seguro e qualificação técnica da proposta.

Orientações para atendimento da devolutiva:
Orienta-se que o Município avalie previamente sua capacidade técnica e operacional para atendimento das adequações solicitadas, bem como priorize os projetos e os ajustes necessários, considerando o prazo estabelecido para esta etapa do processo.
A submissão da versão revisada deverá ser feita exclusivamente através do portal, dentro do protocolo já aberto. O sistema estará disponível para os novos envios a partir do dia 15 de abril, com um **prazo de 72 (setenta e duas) horas corridas (encerramento automático no dia 17 de abril de 2026)**.

Agradecemos o interesse em participar do Programa Respeito à Vida e permanecemos à disposição.

Programa Respeito à Vida (PRaVida)
Havendo necessidade de melhor atendimento, as demandas relacionadas ao Programa serão tratadas pelo canal oficial abaixo.
Dúvidas? Envie para o e-mail: **integracao.municipios@detran.sp.gov.br**

Atenciosamente,
Detran-SP – Departamento Estadual de Trânsito de São Paulo.

ANEXO – PROPOSTAS ADERENTES

ANEXO – PROPOSTAS ADERENTES

NOME DA ÁREA DE INTERVENÇÃO: AV. JÂNIO QUADROS

Identificação da proposta (consolidado pelo Detran-SP[1]): Corredor Seguro - 01

Código PRaVida: PRaVida-CAM-6737-CORRS01-ATE-PB

Código da Revisão: Rev01

Ressalvas e adequações necessárias:

Proposta **enviada previamente** na etapa de **Manifestação de interesse**?

( ) Sim;

(x) Não: foi observada alteração no local da intervenção proposta em relação ao registrado no Relatório Preliminar da Manifestação de Interesse, caracterizando escopo distinto daquele inicialmente apresentado. Esclarece-se que tal divergência não implicará, neste momento, prejuízo à análise da proposta. Entretanto, as ressalvas e adequações indicadas nesta devolutiva deverão ser observadas e atendidas exclusivamente em relação ao projeto efetivamente submetido na etapa de Proposta Técnica, não sendo admitidas novas alterações quanto ao local da intervenção proposta.

Documentação Técnica:

(x) Plano de Trabalho: documento fora de padrão, é necessário adequá-lo de acordo com o modelo disponibilizado e preencher todos os seus campos segundo a orientação do Manual Operacional;

(x) Checklist de Autoanálise de Segurança Viária: necessário adequar de acordo com as orientações do parecer técnico acatadas;

(x) Memorial Descritivo: documento fora de padrão, é necessário adequá-lo de acordo com o modelo disponibilizado e preencher todos os seus campos segundo a orientação do Manual Operacional;

[1] O tipo de abordagem e código podem ter sido alterados pela coordenação do programa, por entendimento técnico da escala adequada do projeto. É fundamental que sejam utilizados em todas as próximas interações para se referir à respectiva proposta e deverão ser replicado em todos os documentos complementares como Plano de Trabalho, Checklist, Memorial Descritivo; Planilha Orçamentária; Cronograma físico-financeiro e desenhos técnicos.

(x) Planilha Orçamentária: documento fora de padrão, é necessário adequá-lo de acordo com o modelo disponibilizado e preencher todos os seus campos segundo a orientação do Manual Operacional;
(x) Cronograma físico-financeiro: documento fora de padrão, é necessário adequá-lo de acordo com o modelo disponibilizado e preencher todos os seus campos segundo a orientação do Manual Operacional;
(x) Desenhos técnicos em formato *.pdf* e *.dwf*: necessário adequar conforme item *2. Recomendações e Ajustes no projeto* deste anexo.
( ) Outros:

Parecer técnico do Projeto

1. Atendimento aos parâmetros do Guia
O projeto, na forma apresentada, atende parcialmente aos parâmetros essenciais do PRaVida, embasados no Guia de Intervenções para Vias Seguras, voltados à proteção de usuários vulneráveis, especialmente pedestres e ciclistas, no(s) ponto(s) analisado(s), em razão de aspectos de projeto que ainda demandam aprimoramento, como a abrangência da área de intervenção, o dimensionamento e organização das faixas, o tratamento de travessias e interseções, e a incorporação de medidas de moderação de tráfego e qualificação dos espaços para pedestres e ciclistas.

2. Recomendações de ajustes no projeto
Para atender aos parâmetros do PRaVida e reduzir os riscos identificados, recomenda-se implementar os **ajustes listados** a seguir. Cada recomendação, embasada no Guia de Intervenções para Vias Seguras, deve ser avaliada e incorporada conforme sua relevância e viabilidade, garantindo maior segurança e conforto para todos os usuários.

Nota técnica sobre os desenhos esquemáticos a seguir:
Os desenhos apresentados neste documento possuem caráter exclusivamente ilustrativo e esquemático, tendo como finalidade apenas indicar possíveis aplicações das ferramentas e soluções previstas no Guia de Intervenções para Vias Seguras. Tais representações não constituem projeto executivo, nem devem ser interpretadas como definição final de geometria, dimensões ou especificações técnicas. As dimensões eventualmente representadas nos esquemas não correspondem a medidas precisas e não substituem o necessário detalhamento técnico. A eventual implementação das soluções sugeridas deverá observar integralmente as normas técnicas federais vigentes aplicáveis, bem como os parâmetros, critérios e orientações estabelecidos no Guia de Intervenções para Vias Seguras.
Compete ao município, por meio de seu responsável técnico, verificar a compatibilidade das intervenções sugeridas com as condições locais e com a infraestrutura viária existente, incluindo,

entre outros aspectos, redes de infraestrutura, drenagem, mobiliário urbano, sinalização, acessibilidade, circulação viária e demais elementos do sistema viário, realizando os ajustes e detalhamentos técnicos necessários para a adequada implantação das soluções. Ressalta-se que eventuais adequações, remanejamentos ou intervenções nesses elementos poderão ser necessárias para a implementação das soluções propostas, não estando necessariamente contempladas no escopo do Programa, devendo sua necessidade e viabilidade ser avaliadas pelo município no desenvolvimento e detalhamento do projeto.

2.1	**Escopo e coerência da intervenção**	
ID	**Item observado**	**Recomendação**
2.1.1	A intervenção não cobre toda a área de influência, deixando trechos críticos sem tratamento.	Recomenda-se ampliar sua extensão nos locais indicados para garantir continuidade e efetividade (ver página 56 - Passo 01 do Guia de Intervenções de Vias Seguras).
2.2	**Larguras, alinhamentos e redistribuição do espaço viário**	
ID	**Item observado**	**Recomendação**
2.2.1	As larguras das faixas não atendem aos parâmetros recomendados.	Recomenda-se ajustar suas dimensões para 2,7 m a 3,0 m para uso misto ou 3,2 m a 3,5 m para ônibus (ver página 121 do Guia de Intervenções de Vias Seguras).
2.2.2	As faixas de trânsito não estão equilibradas, havendo desalinhamento entre o número de faixas de chegada e de saída nos cruzamentos.	Recomenda-se reduzir para o menor número necessário de faixas, evitando desproporcionalidade entre o número de faixas que chegam e saem dos cruzamentos (ver página 121 do Guia de Intervenções de Vias Seguras).
2.2.3	A proposta não reduz áreas residuais nem superfícies amplas de pavimento que favorecem altas velocidades e travessias longas.	Recomenda-se qualificar o desenho viário para reduzir velocidades e distâncias de travessia (ver páginas 54, 55, 68 a 71, 88, 89 e 123 do Guia de Intervenções de Vias Seguras).
2.2.4	A intervenção não converte o excesso de asfalto em áreas para pedestres e/ou ciclistas.	Recomenda-se redistribuir o espaço viário priorizando os modos ativos (ver página 123 do Guia de Intervenções de Vias Seguras).

2.3	Extensões de meio-fio e urbanismo tático	
ID	**Item observado**	**Recomendação**
2.3.1	Não existem extensões de meio-fio no encontro das faixas de estacionamento e travessias de pedestres, de modo a garantir intervisibilidade entre pedestres e motoristas.	Recomenda-se incluir extensões de meio-fio em todas as travessias de pedestres localizadas em vias que possuem faixas de estacionamento. (ver página 123 e 131 do Guia de Intervenções de Vias Seguras).
2.3.2	As extensões de meio-fio não são suficientes para coibir o estacionamento nos 5 m a partir da faixa de travessia.	Recomenda-se ampliar as extensões de meio-fio para garantir visibilidade e segurança nas travessias. (ver página 123 e 131 do Guia de Intervenções de Vias Seguras).
2.3.3	A proposta não prevê proteções físicas junto à nova linha de bordo nas extensões de meio-fio em urbanismo tático.	Recomenda-se incluir balizadores, vasos, floreiras, tachas ou tachões para evitar a invasão por veículos (ver páginas 104 e 105 do Guia de Intervenções de Vias Seguras).
2.4	**Raios de giro, conversões e redução de velocidade em interseções**	
ID	**Item observado**	**Recomendação**
2.4.2	A intervenção não simplifica os movimentos veiculares nos cruzamentos.	Recomenda-se não abrir novos acessos que irão complexificar os movimentos. Os locais indicados devem manter-se fechados para reduzir conflitos e aumentar a segurança (ver páginas 54, 55, 122, 123 e 130 do Guia de Intervenções de Vias Seguras).
2.6	**Travessias de pedestres, visibilidade e refúgio**	
ID	**Item observado**	**Recomendação**
2.6.1	Não há travessias de pedestres em todas as aproximações.	Recomenda-se implantar travessias em todas as aproximações para garantir conectividade e segurança (ver páginas 42, 57 - Passo 05 e 133 do Guia de Intervenções de Vias Seguras).

2.6.2	As travessias não estão posicionadas junto às linhas de desejo e/ou alinhadas às calçadas, comprometendo a intervisibilidade.	Recomenda-se reposicionar as travessias para garantir alinhamento, visibilidade e segurança (ver página 133 do Guia de Intervenções de Vias Seguras).
2.6.4	As travessias de mais de 3 faixas de trânsito, longas (com mais de 10m), em mais de uma etapa, ou em vias arteriais ou coletoras com tráfego intenso não possuem ilhas de refúgio.	Recomenda-se implantar ilhas de refúgio para reduzir a exposição e aumentar a segurança dos pedestres (ver páginas 57 - Passo 05 e 126 do Guia de Intervenções de Vias Seguras).
2.6.6	O projeto não encurta as travessias e/ou evita travessias em condições de baixa visibilidade.	Recomenda-se ajustar o desenho para reduzir a exposição dos pedestres e melhorar a visibilidade (ver páginas 54, 55, 122, 123 e 130 do Guia de Intervenções de Vias Seguras).
2.7	**Ferramentas específicas**	
ID	**Item observado**	**Recomendação**
2.7.1	A minirrotatória proposta não garante o acesso de apenas um veículo por vez e/ou induz a desaceleração e mudança de trajetória.	Recomenda-se revisar o desenho da minirrotatória para permitir o acesso de apenas um veículo por vez, com dimensão suficiente para forçar os motoristas a desacelerar e mudar seu curso, sem prejudicar o percurso de pedestres e ciclistas. (ver páginas 54, 55 e 130 do Guia de Intervenções de Vias Seguras).
2.7.2	As chicanas não apresentam desvio lateral suficiente para forçar a desaceleração e a mudança de trajetória.	Recomenda-se ajustar o desenho da chicana para induzir redução de velocidade e maior controle veicular (ver páginas 54, 55 e 125 do Guia de Intervenções de Vias Seguras).
2.7.4	A sinalização não está adequada às normas vigentes.	Recomenda-se adequar a sinalização horizontal de acordo com os Manuais Brasileiros de Sinalização de Trânsito do Contran, incluindo Marcas Longitudinais, Marcas Transversais e Marcas de Canalização.
3.3	**Corredor Seguro**	

ID	Item observado	Recomendação
3.3.1	As travessias não estão espaçadas em intervalos de até 100 m.	Recomenda-se adequar o espaçamento das travessias da Av Janio Quadros e outras vias do corredor da intervenção em até 80 m para garantir acessibilidade e segurança aos pedestres (ver páginas 65, 76 - Passo 03, 133 do Guia de Intervenções de Vias Seguras).
3.3.3	Não há ferramentas de moderação de tráfego suficientes nos espaçamentos recomendados.	Recomenda-se implantar medidas a cada 75 m para induzir a redução da velocidade praticada (ver páginas 26 e 29 do Guia de Intervenções de Vias Seguras).

3. Riscos remanescentes

Caso o projeto seja implantado sem os ajustes recomendados, permanecem riscos relevantes, como travessias extensas ou com menor nível de proteção, situações de conflito nos cruzamentos, condições de visibilidade que podem ser aprimoradas e contextos que podem favorecer velocidades mais elevadas, comprometendo a segurança viária e contrariando os princípios do Sistema Seguro.

4. Devolutiva dos municípios

Para cada recomendação listada no item 2, o município deverá indicar se irá incorporá-la ou não ao projeto. Caso não a incorpore, deve apresentar justificativa técnica ou operacional para a decisão. Essa devolutiva permite avaliar o alinhamento do projeto com os princípios do PRaVida e documentar os ajustes implementados ou as restrições identificadas.
Acesse **aqui** o modelo para devolutiva deste parecer técnico.

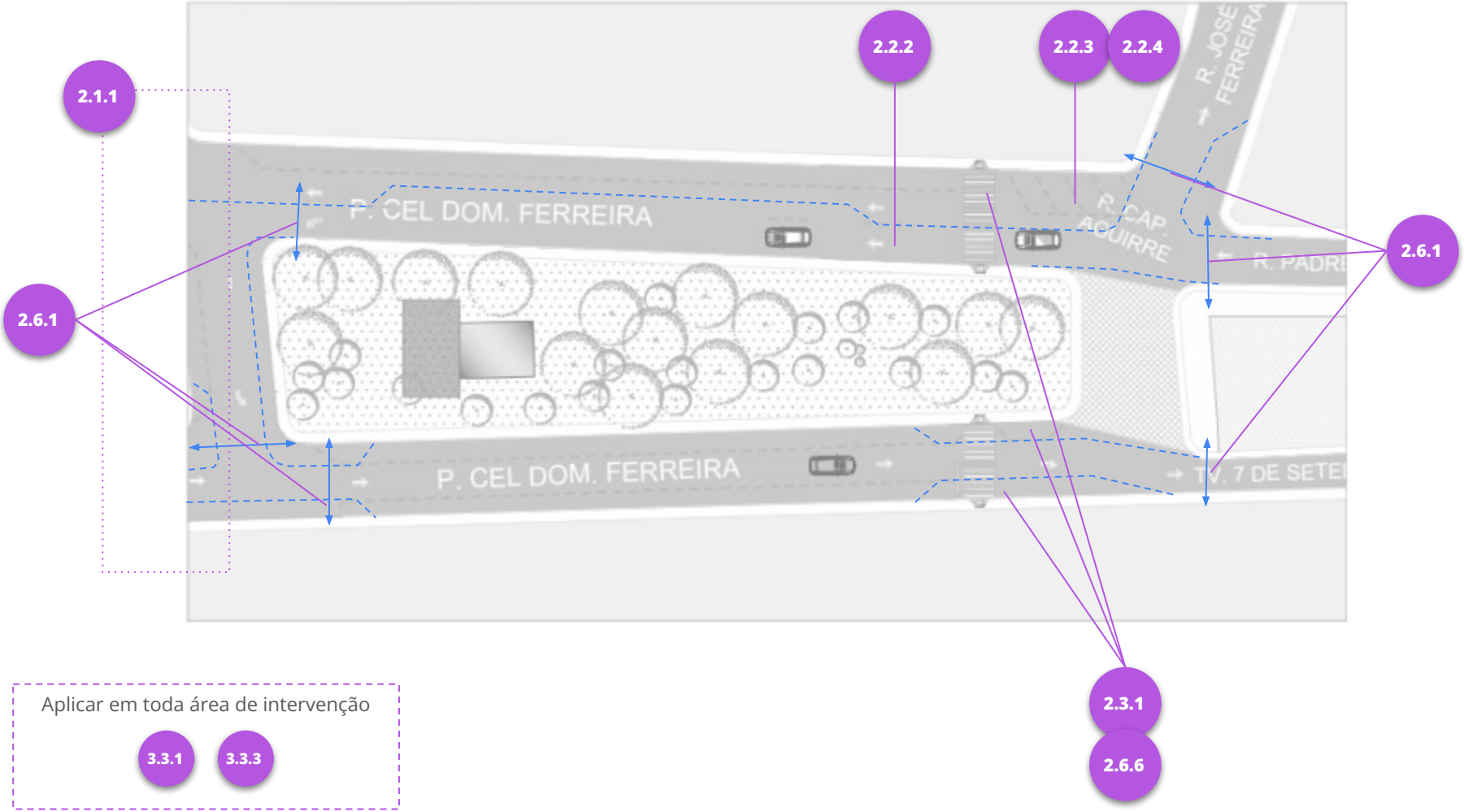

Aplicar em toda área de intervenção

3.3.1 3.3.3

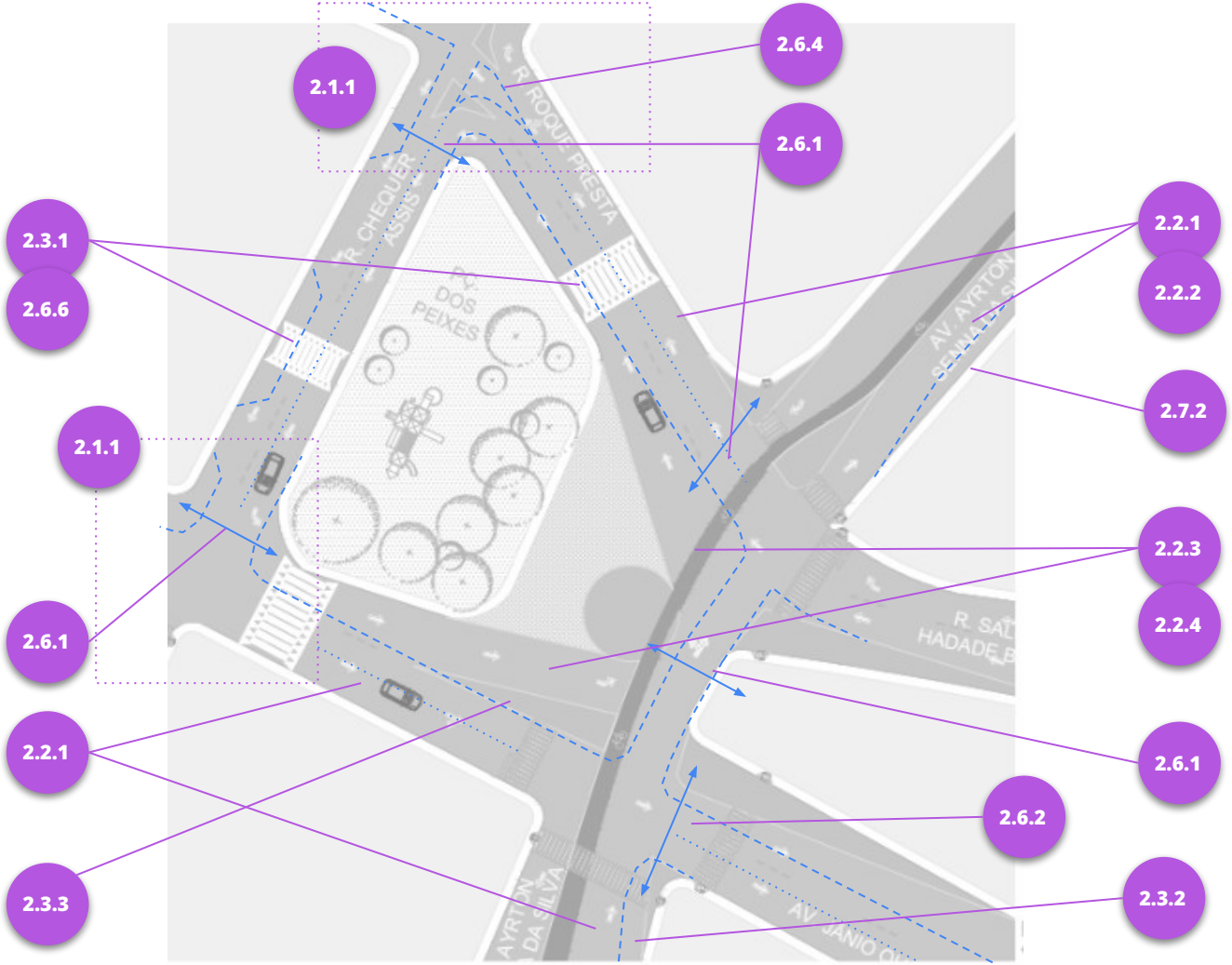
2.1.1
2.6.4
2.6.1
2.3.1
2.6.6
2.2.1
2.2.2
2.7.2
2.1.1
2.2.3
2.2.4
2.6.1
2.2.1
2.6.1
2.6.2
2.3.3
2.3.2
R. ROQUE PRESTA
R. CHEQUER ASSIS
PQ. DOS PEIXES
AV. AYRTON
R. SAT HADADE
AV. JÂNIO QU
AYRTON DA SILVA

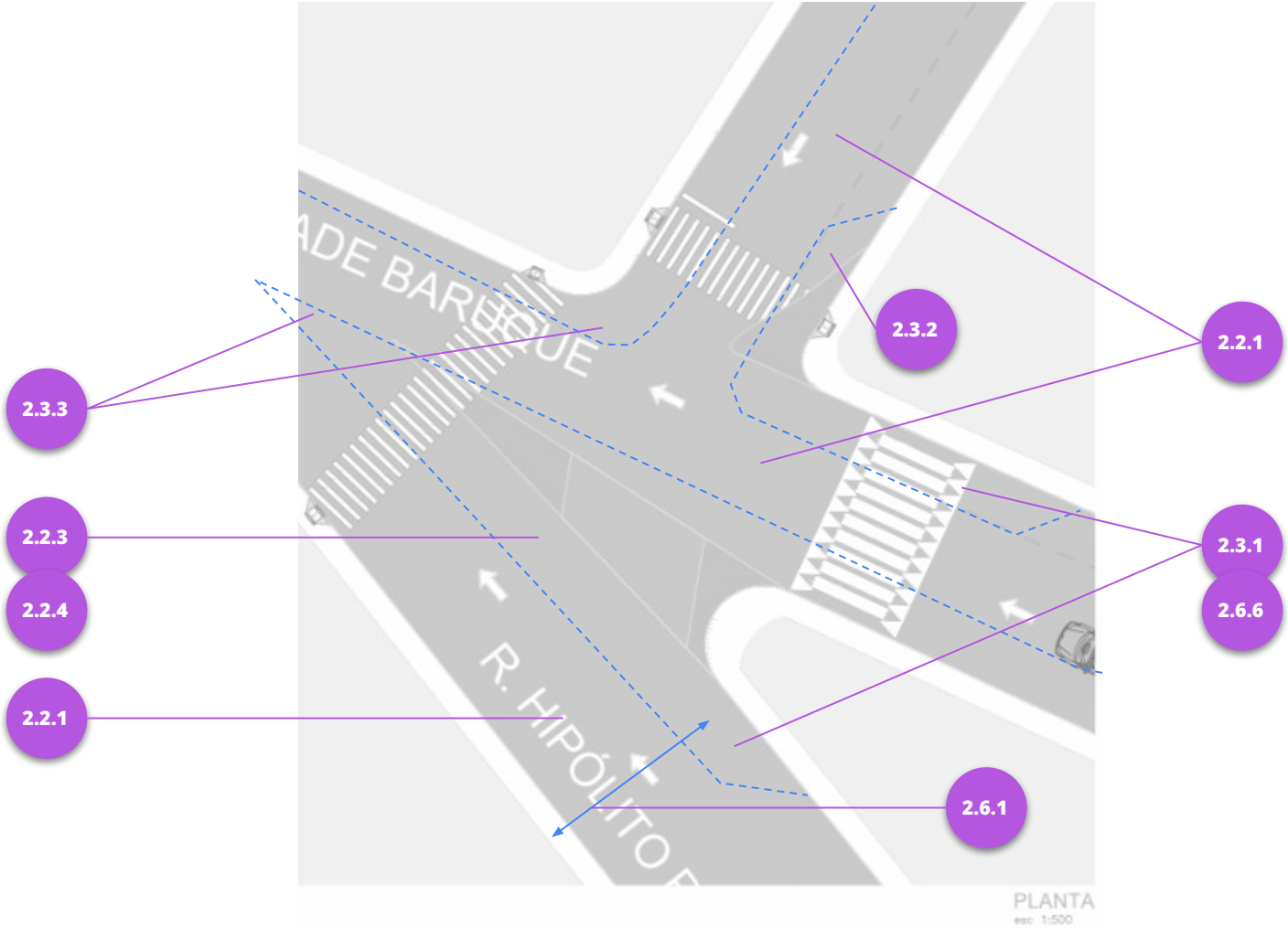
ADE BARRIQUE
R. HIPÓLITO
2.3.3
2.2.3
2.2.4
2.2.1
2.3.2
2.2.1
2.3.1
2.6.6
2.6.1
PLANTA
esc 1:500

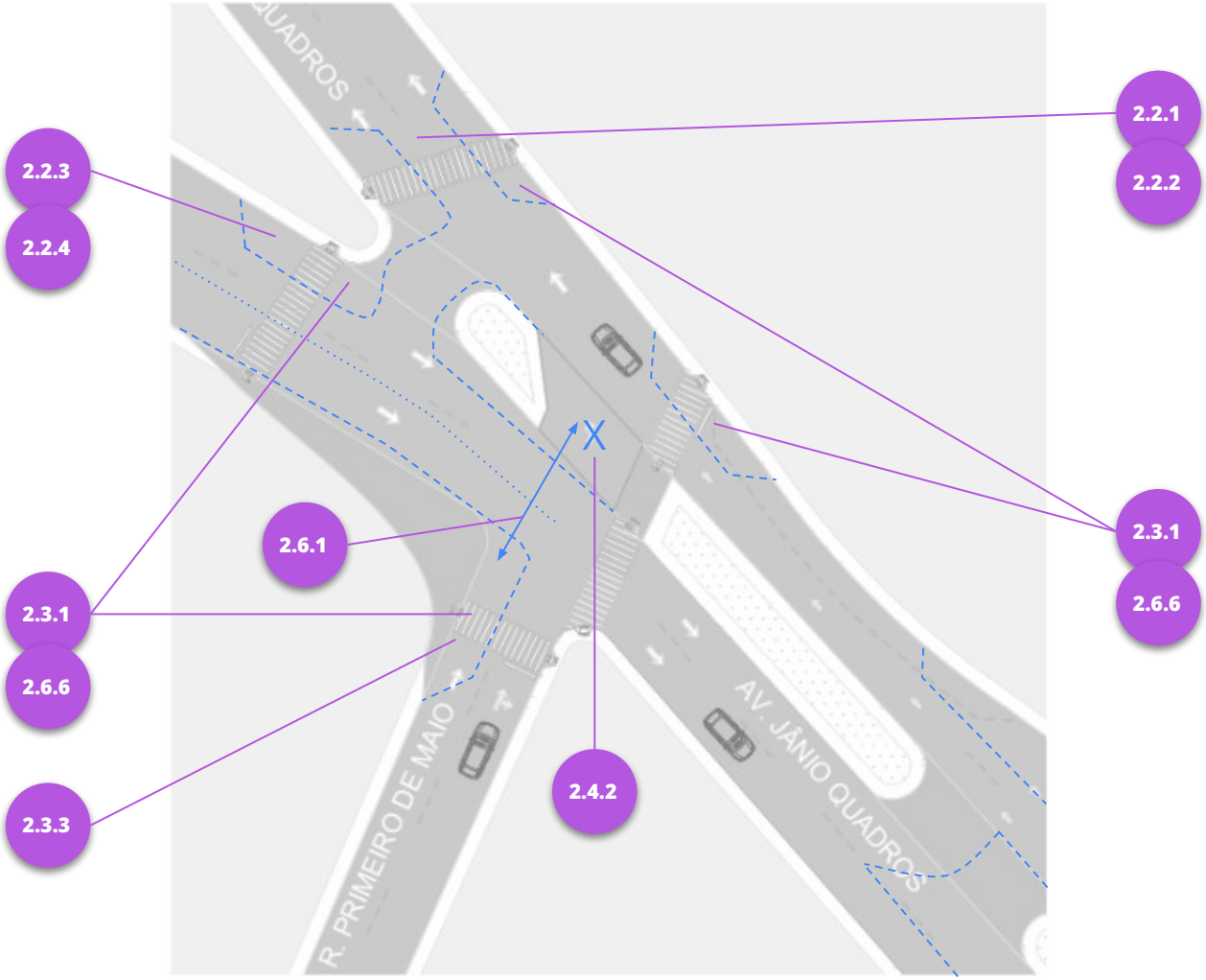
QUADROS
2.2.1
2.2.2
2.2.3
2.2.4
X
2.6.1
2.3.1
2.6.6
2.3.1
2.6.6
2.3.3
2.4.2
R. PRIMEIRO DE MAIO
AV. JÂNIO QUADROS

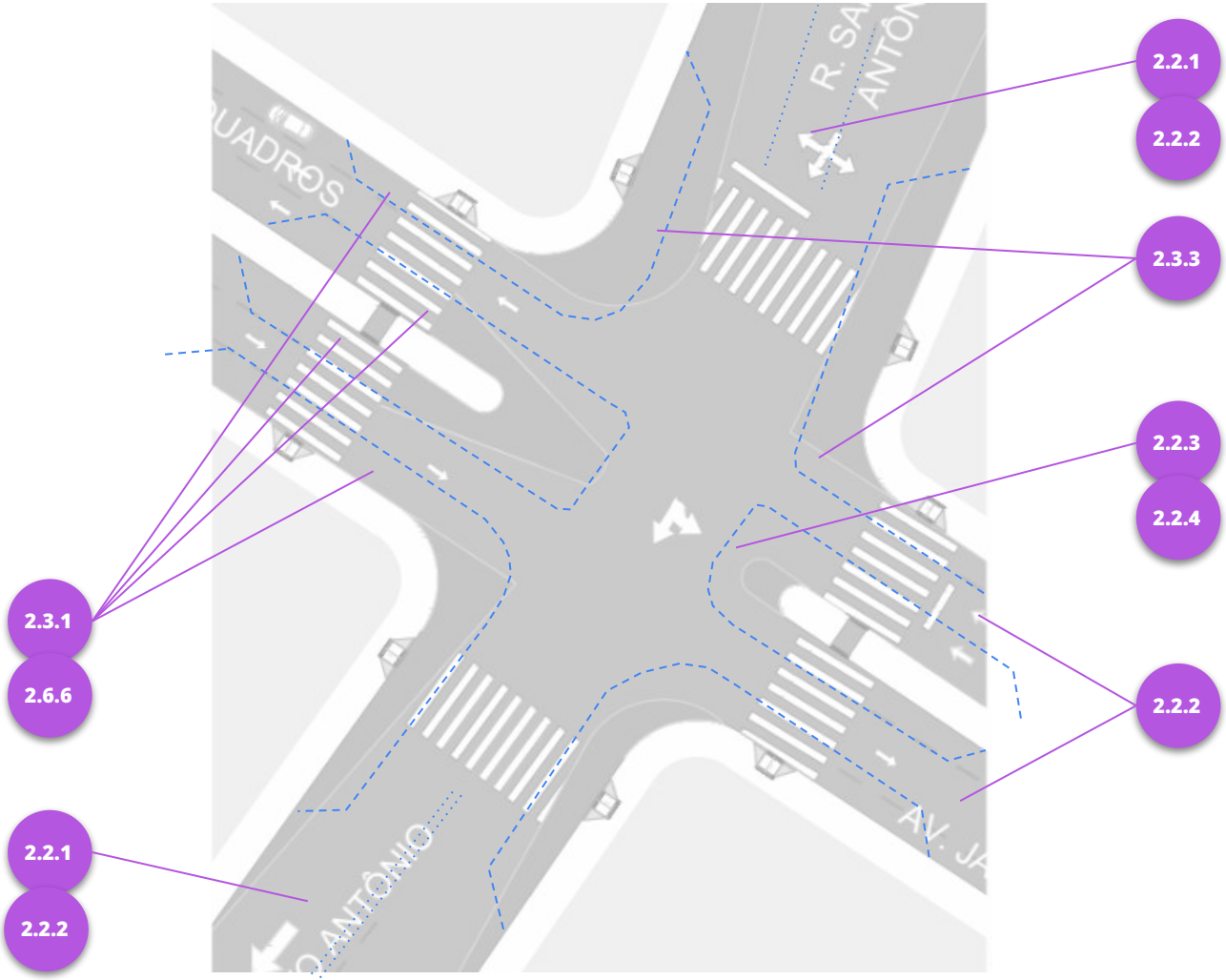
2.2.1
2.2.2
2.3.3
2.2.3
2.2.4
2.3.1
2.6.6
2.2.2
2.2.1
2.2.2
R. SA
ANTÔN
UADROS
AV. JA
O ANTÔNIO

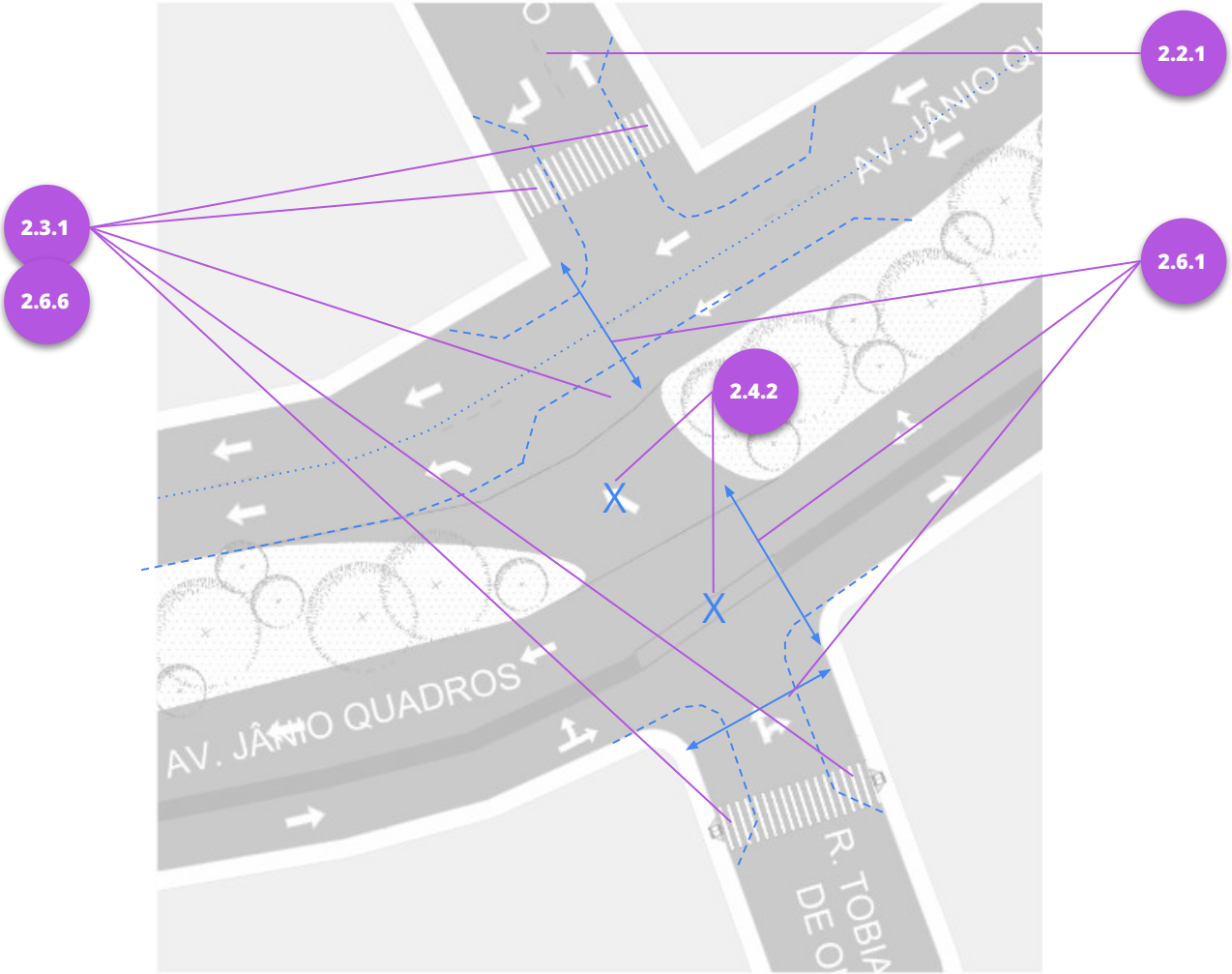
2.2.1
2.3.1
2.6.6
2.6.1
2.4.2
X
X
AV. JÂNIO QUADROS
AV. JÂNIO QU
R. TOBIA
DE O

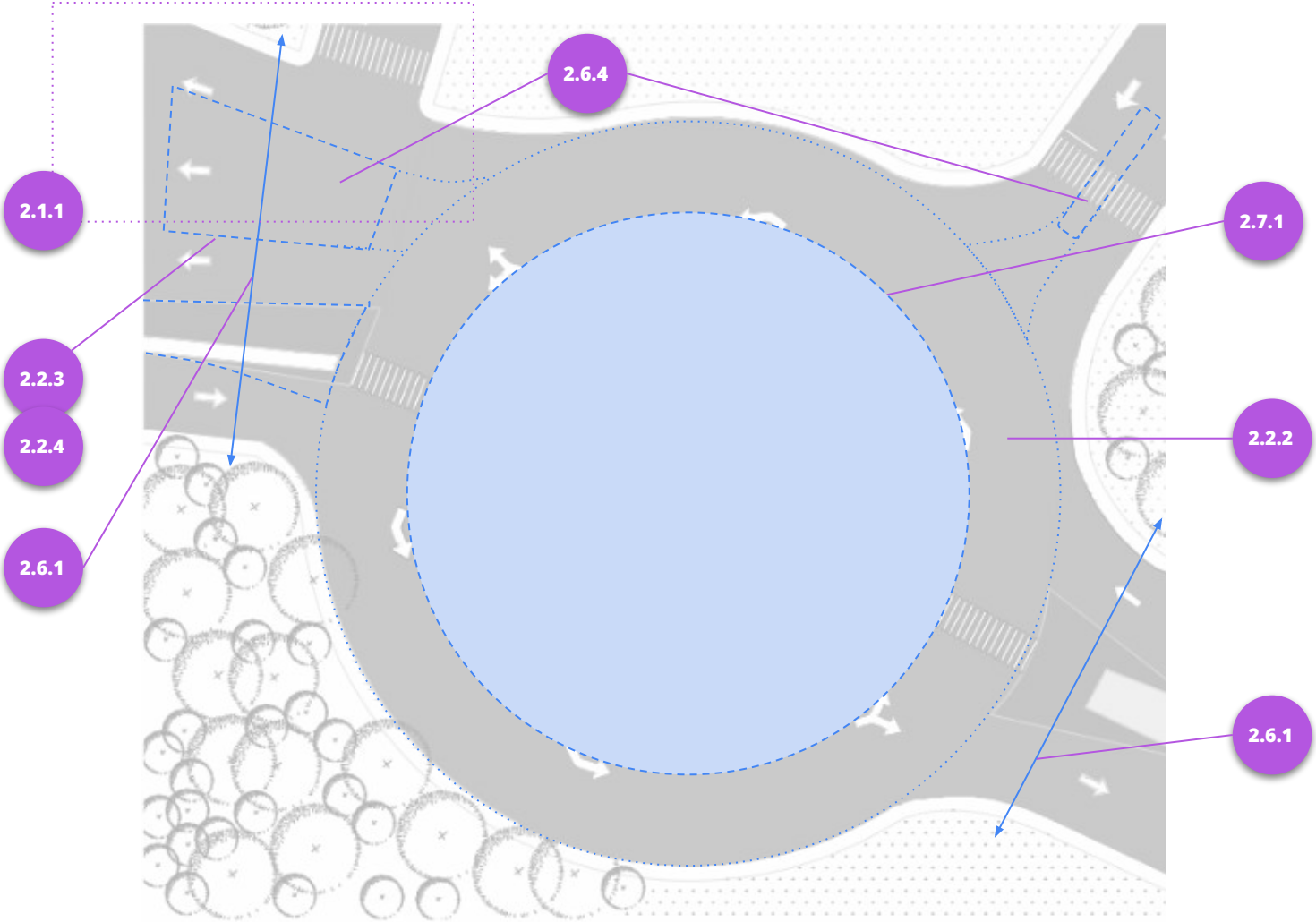
2.6.4
2.1.1
2.7.1
2.2.3
2.2.4
2.2.2
2.6.1
2.6.1